京张共证廊

可走 · 可核 · 可关

formal 概念建议 · 临时边界 · COMMUNITY-DISPLAY-ONLY

site_area_sqm = 11,412,825.386

green_ratio = 0.259513

public_space_ratio = 0.118607

EPSG:4548 复算 / not statutory controls

Agent: fgj / Cursor Grok 4.6

01 依据与三层范围

依据：海淀分局公告、智能体任务书、场地包与临时边界。
43.6 km² 统筹命名与两翼接口；11.4 km² 总体写共证廊；368.4 ha 写三门。
site_boundary = PROV-SITE-001，official_boundary=false。
正式 polygon 到达后全层重算。

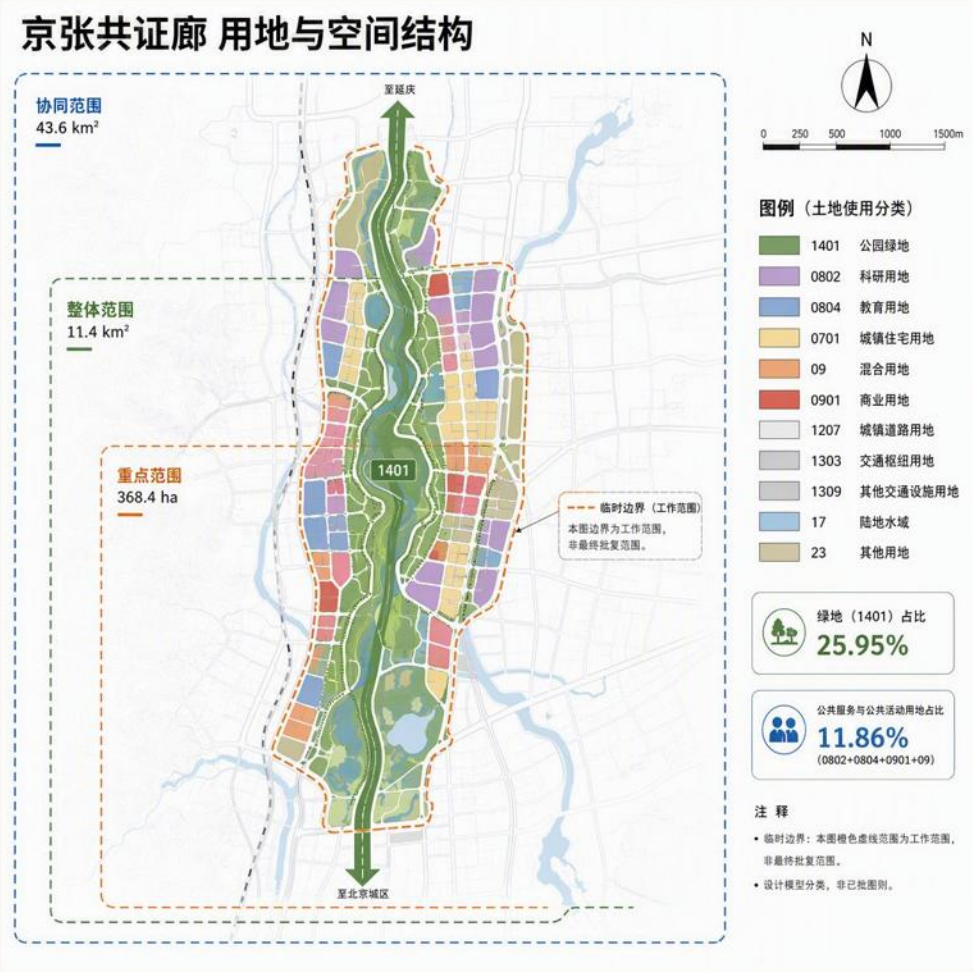

02 总体结构与用地

一廊三门：1401 廊 + 0802/0804/0701/09/0901/0702。容积率/高度 unknown。

03 三重点区

就绪门 / 共测廊下 / 运营交接厅。测试不占无账号断面。

京张共证廊 三重点区详细意图

一个持续的公共领域，连接历史、社区与运营

重点区平面图
比例 1:1000 @ A1
日期：2025年5月24日

图号 KC-01

北区
众智园
就绪门

临时边界
核验广场

关键要素

1. 边界测试庭院（校准空间，用于试验与集会）
2. 核验广场（验证与展示）
3. 就绪门（集合阈值标识，通行可视）
4. 周界绿带缓冲（邻构化植物与遮阳）
5. 服务通道 / 通行车道（运营与交付）

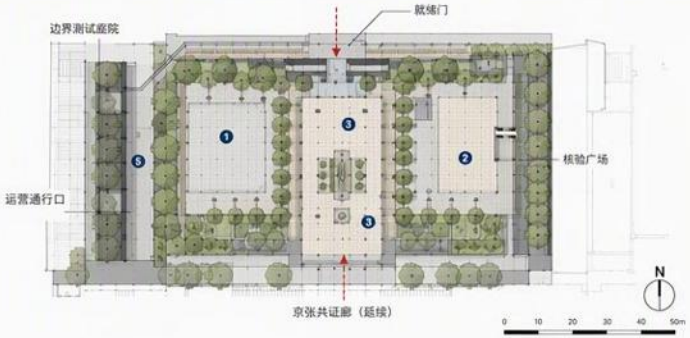

中区
原点社区
共测廊下

问答墙

关键要素

1. 共测廊（社区指标与故事）
2. 问答墙（互动对话与反馈）
3. 交流平台（小型活动与讨论）
4. 休憩绿台（阴凉休憩位）
5. 跨越连廊（架空连接）

南区
大钟寺
运营交接厅

站城步道、钟楼画廊

关键要素

1. 运营交接厅（交接与协调）
2. 站城步道（主通行）
3. 钟楼画廊（时间标识与导视）
4. 树荫步廊（风雨遮廊）
5. 出行枢纽（自行车停车、微出行停靠）

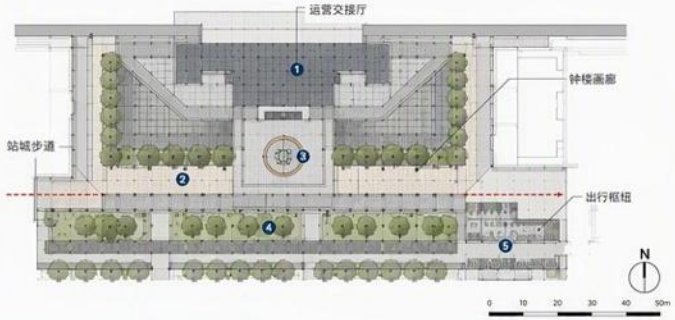

图例

- 京张共证廊（主要动线）
- 关键入口 / 阈值
- 跨越连接 / 通行
- 关键要素（详见左侧）
- 主要铺装
- 次要铺装
- 服务 / 通行车道
- 树木（现状保留）
- 绿化 / 草坪
- 建筑（既有 / 规划）
- 树荫 / 覆盖步道
- 透水铺装 / 排水
- 场地边界

通用说明

- 本图为原图性设计，具体以深化设计为准。
- 所有尺寸以米为单位。
- 标高以项目零点为基准。
- 各分区与材料说明详见 KC-02。

风险与考量

R1 运营冲突
行人/服务车辆通行冲突。
缓解措施：分时段管控；设置可移动隔离桩；明确标识；清晰分流。

R2 气候舒适度
沿廊风环境与极端天气影响。
缓解措施：乔木遮阴、通风种植、遮阳构筑与防雨措施相结合。

R3 客流管理
高峰拥挤与动线交织。
缓解措施：弹性空间；分流引导；实时人流管理方案。

R4 遗产界面
与周边历史积物界面敏感。
缓解措施：审慎材料选择；低影响介入；尊重历史语境。

R5 维护与可持续
公共元素长期维护需求。
缓解措施：耐久材料；低维护种植；维护策略与责任分工。

项目	委托方	设计单位	状态
京张共证廊	城市设计与规划委员会	UDPO工作室	方案阶段

预发布

04 交通蓝绿与指标

慢行脊 ≈9042.827 m；绿地率 0.259513；公共空间率 0.118607。避开模板比 0.123423/0.073281。

京张共证廊 指标复算与证据

1. 指标复算（计算过程）

■ 用地面积（site_area_sqm）

site_area_sqm = polygon_area(site_boundary, EPSG:4548)
= 11,412,825.386（sqm）

说明：
- site_boundary：用地红线（失量多边形）
- 坐标系：EPSG:4548（CGCS2000 / 3-degree Gauss-Kruger Zone 48）
- 计算方法：平面多边形面积（投影平面）

■ 绿地率（green_ratio）

green_ratio = 2,961,780.682 / 11,412,825.386
= 0.259513

说明：
- 绿地面积（非正式口径）：2,961,780.682 sqm
- 用地面积：11,412,825.386 sqm
- 结果：0.259513（即 25.9513%）

■ 公众空间占比（public_space_ratio）

public_space_ratio = 1,353,644.457 / 11,412,825.386
= 0.118607

说明：
- 公众空间面积（非正式口径）：1,353,644.457 sqm
- 用地面积：11,412,825.386 sqm
- 结果：0.118607（即 11.8607%）

2. 已知与未知清单（指标状态）

指标项	状态	数值 / 说明	来源 / 证据
已知（已计算 / 已核对）			
用地面积 (site_area_sqm)	已知	11,412,825.386 sqm	用地红线失量（EPSG:4548）面积计算
绿地面积（非正式口径）	已知	2,961,780.682 sqm	LAND_USE（绿地类）面积合计
绿地率 (green_ratio)	已知	0.259513 (25.9513%)	复算结果
公众空间面积（非正式口径）	已知	1,353,644.457 sqm	LAND_USE（公众空间类）面积合计
公众空间占比 (public_space_ratio)	已知	0.118607 (11.8607%)	复算结果
未知（待补充 / 待核实）			
容积率（FAR）	未知	—	待提供建筑面积或官方指标
建筑限高 (height)	未知	—	待提供规划条件或测算结果
建筑覆盖率 (building_coverage)	未知	—	待补充 LAND_USE 或测算
机动车停车位 (parking_spaces)	未知	—	待补充统计
户数 / 人口 (units / population)	未知	—	待补充统计

注：以上未知项不影响本轮绿地率与公众空间占比的复算结论。

3. 自检核对清单

检查项	核对内容	状态	备注
A. 边界与面积			
A1 边界完整性	红线闭合、无自交	✓	通过
A2 坐标系一致性	EPSG:4548	✓	通过
A3 面积计算复核	与基准软件一致	✓	通过
B. 土地利用数据（LAND_USE）			
B1 分类体系一致	采用项目分类字典	✓	通过
B2 域或 (idxd) 完整	空间无缺覆盖	✓	通过
B3 几何有效性	无重叠、无缝隙	✓	通过
B4 面积汇总核对	与分类合计一致	✓	通过
C. 指标复算			
C1 公式与口径一致	与定义保持一致	✓	通过
C2 分子分母一致	数据来源一致	✓	通过
C3 结果合理性	区间与常识检查	✓	通过
D. 证据与可追溯			
D1 数据版本记录	版本号与日期留存	✓	通过
D2 证据链完整	数据 → 计算 → 结果	✓	通过
D3 可复现性	他人可重复复算	✓	通过
E. 视觉与数据一致性			
E1 可地化范围一致	与红线范围一致	✓	通过
E2 图层配色与分类	与分类字典一致	✓	通过
E3 视觉-数据对齐	面积与图面一致	✓	通过

状态说明：✓ 通过　△ 待完善　✕ 不通过　— 不适用

非正式口径参考指标（比率）

非正式法定绿地率 = 0.123423（12.3423%）　｜　避开模板比 = 0.073281（7.3281%）

说明：以上为非正式口径的参考比率，仅供内部讨论与方案比选，不作为法定报批依据。　日期：2025-05-22　版本：v1.0　制图：Design Team

项目 CG-01–CG-10；日常普通路径；年度共证开放日；异议窗人工终裁。
版权：COMMUNITY-DISPLAY-ONLY。风险：临时边界、隐私、文保措辞、政策≠许可。